Migración Interna en los municipios de Bolivia*

Fichas Municipales con el Censo de Población 2012

Alvaro Chirino Gutierrez**

Instituto de Estadística Teórica y Aplicada
Universidad Mayor de Andres

2016

Resumen

El documento emplea el concepto de *visualización de datos* para ilustrar sus resultados, se elaboran fichas departamentales y municipales para mostrar los flujos migratorios y se presentan estadísticas que caracterizan a los inmigrantes y emigrantes. Se considera la migración interna de toda la vida y se emplea los datos del Censo Nacional de Población y Vivienda 2012 que se realizo en Bolivia.

El documento no busca realizar un análisis sobre los datos, lo que se pretende es poner a disposición de todos, estadísticas de la migración interna y que a partir de ellas se generen debates locales, análisis demográficos y se incremente la demanda por este tipo de información.

Palabras clave: Migración interna, Mapas temáticos, Gobiernos subnacionales, Visualización de datos

*Este documento esta en el marco del proyecto de investigación: "Estimación en pequeñas áreas: Patrones demográficos, indicadores de bienestar y pobreza multidimensional, una aplicación para los municipios de Bolivia"

**Comentarios a achirino@aru.org.bo

1. Motivación

A partir de 2010 con la promulgación de la ley marco de autonomías Andres Ibañes, los gobiernos sub nacionales (Departamentos y Municipios) en Bolivia ganaron mas atribuciones y competencias, este proceso autonómico trae consigo de forma implícita la necesidad de información en distintas áreas a nivel local. En la actualidad la cantidad de información estadística relacionada a temas sociales (bienestar, demográficos, etc.) que se genera a nivel de las estructuras político administrativas se concentran fuertemente en el estado central y la información para los niveles mas bajos es escasa, la figura 1 muestra un esquema de la brecha de información que existe entre estos niveles. Por esta razón un Censo de Población siempre es una oportunidad para explotar la mayor cantidad de información disponible en temáticas que aborde el censo y a niveles que una encuesta normalmente no llega, la figura 2 muestra tres encuestas con tópicos específicos que realizo el INE en el ultimo periodo intercensal y los niveles de representatividad con el que fueron diseñados.

Figura 1: Brecha de Información entre el estado central y los gobiernos sub nacionales

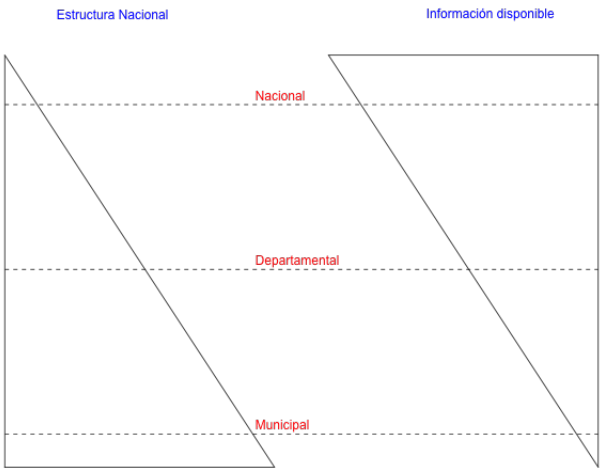

Fuente: Elaboración del autor

Entender como las poblaciones se movilizan de forma espacial dentro de un país entre las distintas regiones que existen es un tema que en demografía se conoce como **migraciones internas**, la realización de un censo de población permite tener un detalle mas profundo de estos movimientos y da la oportunidad de caracterizar a las personas que se mueven. Las dos unidades administrativas mas relevantes actualmente para la toma de decisiones son los departamentos y los municipios, existen 9 departamentos y 339 Municipios. Con el censo 2001 en Bolivia se generaron varios documentos que exploraban la migraciónde formas distintas, entre ellos el *Perfil Migratorio de Bolivia* (Morató, 2011), *Las migraciones en Bolivia* (Bustillos, Layme, Morató, y Gordonava, s.f.), entre algunos, sin embargo, son escasos los documentos que exploran la migración en alguna dimension a nivel de cada uno de los municipios o departamentos. En base a ello, este documento abordara la migración interna, mas propiamente la migración interna de toda la vida, se empleara el censo de población y vivienda 2012 y los resultados serán a nivel departamental y municipal.

Figura 2: Encuestas especializadas del INE en el ultimo periodo Intercensal

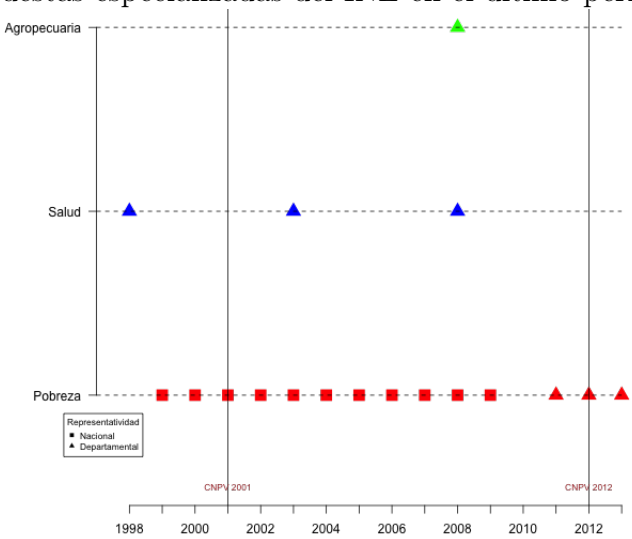

Fuente: Elaboración del autor

El documento empleara el concepto de *visualización de datos* para ilustrar sus resultados, para ello se crearan fichas departamentales y municipales, donde se tengan datos de los inmigrantes y emigrantes respecto a sus características básicas y se pueda visualizar de forma espacial los flujos migratorios. El documento no busca realizar un análisis sobre los datos que se presenten, lo que se pretende es poner a disposición de todos, estadísticas de la migración interna y que a partir de ellas se generen debates locales, análisis demográficos y se incremente la demanda por este tipo de información.

Este documento esta en el marco del proyecto de investigación: "Estimación en pequeñas áreas: Patrones demográficos, indicadores de bienestar y pobreza multidimensional, una aplicación para los municipios de Bolivia" del Instituto de Estadísticas Teórica y Aplicada de la Carrera de Estadística de la Universidad Mayor de San Andres. El documento presenta en 2 los objetivos del trabajo, en 3 algunos conceptos importantes, en 4 los datos y criterios empleados en el trabajo, en 5 la metodología empleada para la creación de los indicadores que se emplearon para las figuras empleadas en las fichas departamentales y municipales, en 6 se desarrolla los resultados principales y finalmente en 7 se listan las conclusiones del trabajo.

2. Objetivos y alcances

El objetivo de este documento es:

> Emplear la base de datos del Censo Nacional de Población y Vivienda 2012 para crear indicadores y plasmarlos en fichas departamentales y municipales sobre la migración interna de toda la vida.

En cuanto a los alcances:

1. Se trabaja con información del Censo de Población y Vivienda 2012
2. El trabajo se limita a la migración interna de toda la vida

3. Se considera solo a las personas que habitan en viviendas particulares (se omite a las viviendas colectivas)

4. Las fichas municipales serán para los 9 departamentos y los 339 municipios de Bolivia

3. Conceptos importantes de migración

Según el Diccionario Demográfico Multilingüe de la Unión Internacional para el Estudio Científico de la Población[1] "Se da el nombre de migración o movimiento migratorio, al desplazamiento, con traslado de residencia de los individuos, desde un lugar de origen a un lugar de destino o llegada y que implica atravesar los límites de una división geográfica". Entendiendo como migración interna ese mismo desplazamiento, pero al interior de un país y entre sus unidades político administrativas (UPA).

Existen también 2 principales conceptos dentro de la definición de migración: la inmigración y la emigración; la inmigración puede entenderse como el volumen de personas que llegan a una unidad político administrativa y provienen de otra y la emigración es el volumen de personas que salen de una unidad político administrativa y se van a otras. En base al tiempo de permanencia en la UPA después del desplazamiento se define la:

- **Migración de toda la vida:** Total de personas que residen en una UPA distinta a la de UPA de nacimiento.
- **Migración reciente:** Total de personas que residen en un UPA distinta a la residencia que tenían 5 años antes
- **Migración habitual:** Total de personas que estan en un UPA distinta a la que reciden habitualmente

Otro indicador importante es el Saldo Migratorio, este se define como:

$$SM(i) = total(inmigrantes(i)) - total(emigrantes(i)) \tag{1}$$

Con $SM(i)$ el saldo migratoria de la UPA i. Este indicador puede ser $SM(i) > 0$ lo que implica que la UPA i es una unidad "atractiva" para desplazarse y si $SM(i) < 0$ implica que la unidad i es "expulsora" puesto que los que se van (emigrantes) son mayores a los que llegan (inmigrantes).

Las llamadas matrices de migración son otro concepto que incluyen dentro de ellas las UPA y los desplazamientos entre ellas, es decir, permite ver la inmigración y emigración de las UPA, el cuadro 1 muestra la forma en esquema de esta matriz, los componentes de la matriz son: (1) las corrientes o flujos $i \neq j$ (2) la diagonal y (3) las marginales.

Para la construcción de esta matriz para el censo 2012 se emplea la pregunta 32 del cuestionario censal, esta se muestra en la figura 3. Esta permite identificar el departamento y el municipio en el cual nació, si la persona declara haber nacido en otro lugar

[1] `http://www.demopaedia.org/tools/spip.php?page=generate_dictionary&edition=es-i&format=html`

Cuadro 1: Matriz de migración

Lugar de Residencia Actual	Lugar de residencia ANTERIOR				Total
	UPA_1	UPA_2	$\dots$	UPA_d	
UPA_1	N_{11}	N_{12}	$\dots$	N_{1d}	$N_{1.}$
UPA_2	N_{21}	N_{22}	$\dots$	N_{2d}	$N_{2.}$
$\dots$	$\dots$	$\dots$	$\ddots$	$\dots$	$\dots$
UPA_d	N_{d1}	N_{d2}	$\dots$	N_{dd}	$N_{d.}$
TOTAL	$N_{,1}$	$N_{,2}$	$\dots$	$N_{.d}$	$N_{..}$

del país distinto en el cual vive el día del censo, sin embargo, la forma de la pregunta suele tener algunas fuentes de error debido a que muchas personas pueden entender de forma ambigua la pregunta y tender a sub estimar o sobre estimar el detalle del enunciado.

Figura 3: Pregunta de migración de toda la vida en el Censo 2012

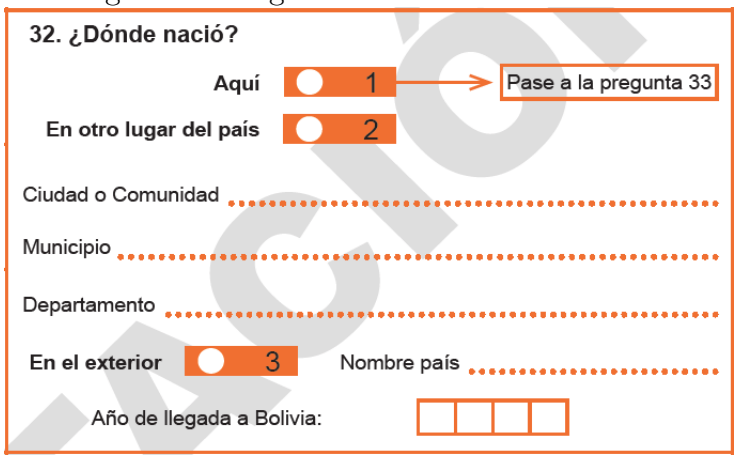

Por ultimo, las fuentes de información para obtener los indicadores mencionados pueden ser: (1) Registros administrativos, (2) Encuestas Nacionales y (3) Censo de Población, cada una con características particulares que permiten conocer los indicadores de migración con distintos niveles y periodicidad.

4. Datos

Se emplea el Censo de Población y Vivienda 2012 que realizo el Instituto Nacional de Estadística de Bolivia, se utilizan las variables que corresponden a las personas, adicionalmente se emplean mapas espaciales de los departamentos y los municipios.

Dado que el tema central del documento es migración interna, se emplea la pregunta 32 del cuestionario censal y la variable de ubicación actual de la persona entrevista para marginar correctamente a los inmigrantes y emigrantes según departamentos o municipios.

5. Metodología

Esta sección detalla las consideraciones realizadas para identificar a los inmigrantes y emigrantes de toda la vida empleando los datos del censo 2012, la construcción de la matriz de migraciones y las variables elegidas para crear el perfil de los inmigrantes o emigrantes.

5.1. Matriz de migración

Para la construcción de esta matriz se empleo la pregunta 32 de la boleta censal, con las siguientes consideraciones:

- solo se considero a las personas que declararon haber nacido en otro lugar del país, es decir, no forman parte de la matriz las personas que nacieron en el exterior o nacieron en el mismo lugar de residencia. Tener en cuenta que para el caso de los departamentos existen personas que migraron entre municipios dentro de un mismo departamento, de igual forma en el caso de los municipios, es posible que existan migraciones entre las comunidades dentro de un mismo municipio, por ello la diagonal de la matriz no sera nula, si no contendrá el movimiento dentro de los departamentos o municipios.

- si la persona declara haber nacido en otro lugar del país, el lugar en el que nació se lo registro en una pregunta abierta, es decir, el empadronador anotaba el nombre del lugar de nacimiento (Departamento, Municipio, etc.). La base de datos esta codificada, de tal forma que es posible identificar el departamento, la provincia y el municipio, sin embargo, existen observaciones en las cuales no se pudo codificar el lugar de nacimiento y tienen un código 99, esto ocurre en las provincias y municipios, la razón puede deberse a una declaración errónea, esto se da a nivel de las provincias y municipios. Para la construcción de la matriz de migración no se consideran estas observaciones a nivel municipal.

- Con la matriz de migraciones identifico a las personas en inmigrantes y emigrantes de toda la vida.

Una de las aplicaciones de la matriz de migraciones se presenta en la figura 4 que muestra el flujo de migrantes entre los departamentos, este tipo de representaciones gráficas ofrecen una mayor perspectiva a la que se lograría analizando la matriz (ver cuadro 2).

5.2. Variables para el perfil de migración

Considerando trabajos sobre migración interna en otros países Kumar, 2004, Vega, 2007, Bott, 2014 entre otros y las preguntas del cuestionario censal, se eligieron las siguientes variables para realizar el perfil:

- Sexo
- Edad

Figura 4: Flujo Departamental para la Migración interna de toda la vida, Bolivia 2012

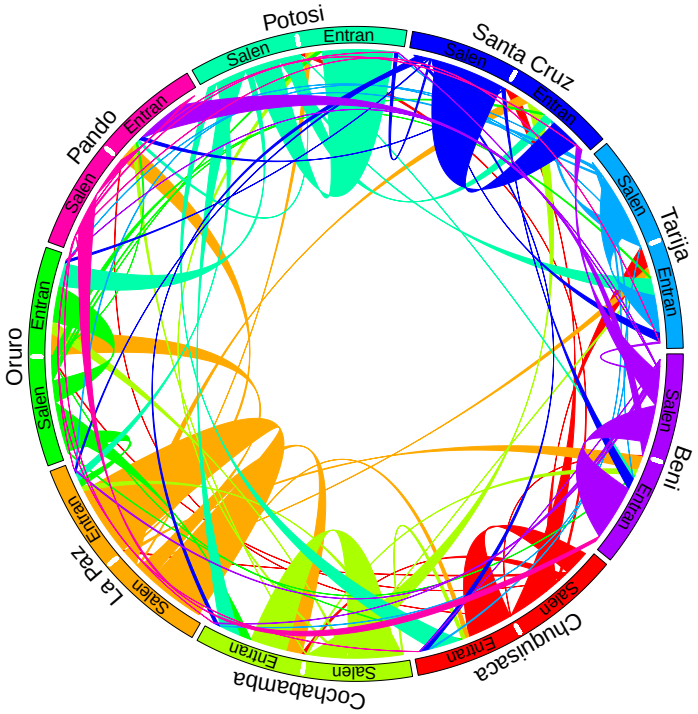

Cuadro 2: Matriz de migración de toda la vida para los departamentos

Departamento	CH	LP	CB	OR	PT	TJ	SC	BN	PD
Chuquisaca	66378	5731	4789	3823	42192	5802	11898	941	116
La Paz	9611	351446	24213	32656	34854	5535	12632	11734	1162
Cochabamba	18974	77715	181168	61384	104060	4082	25006	9563	602
Oruro	1581	24222	13550	40959	25731	1012	3131	389	68
Potosi	9562	9209	9496	10432	125168	3587	5407	352	47
Tarija	33905	10453	4772	4022	27073	59827	13780	2419	181
Santa Cruz	110120	80612	126801	28445	66914	23744	227005	57616	1497
Beni	1452	16957	6857	1895	2839	648	13474	67344	7411
Pando	627	8648	2226	941	1077	541	1914	25058	8437

- Categoría ocupacional
- Actividad principal
- Identificación indígena
- Años de educación

Una vez definidas las variables de perfil y las matrices de migraciones, se diseñaron las figuras y los mapas para las fichas departamentales/municipales, se diseñaron para inmigrantes y emigrantes. El objetivo de estas figuras es brindar información rápida, útil, técnicamente calculada y amigable para los distintos usuarios.

En los siguientes apartados se describen las consideraciones realizadas y los tipos de gráficos que se diseñaron para las fichas para las variables consideradas. El calculo de los indicadores y la matriz de migraciones se realizo en *Stata*, todas las figuras fueron diseñadas en *R* y las fichas y este documento se compilaron en Latex[2].

5.2.1. Variable: Edad

Corresponde a la pregunta 25 del cuestionario censal, en la base de datos la información esta disponible en edades simples. Los gráficos construidos son:

- Gráfico de barras en porcentaje para las edades agrupadas en quinquenios, con un recuadro del promedio de edad.
- Gráfico de barras vertical en porcentaje para las edades agrupadas en grandes grupos (1) $0 - 14$, (2) $15 - 64$ y (3) 65 y más, con características de mosaico (barras proporcionales al porcentaje).

Los dos gráficos se encuentran en la ultima fila de las fichas municipales.

5.2.2. Variable: Sexo

Corresponde a la pregunta 24 del cuestionario censal, el gráfico construido es un *radial pie*, es una mezcla de un gráfico de araña y torta. Se encuentran en los costados de la parte central de las fichas.

5.2.3. Variable: Condición de ocupación

Corresponde a la pregunta 43 del cuestionario censal, esta pregunta es de tipo categórica y tiene 6 categorías. El gráfico que se empleo fue uno de araña, se usaron otros nombres en las categorías, esto con el fin de mejorar la interpretación, las categorías de la variable y los nombre usados fueron:

Pregunta 43	Nuevos nombres
Obrera(o) / Empleada(o)	Asalariado
Trabajadora(or) por cuenta propia	Cuenta Propia
Empleadora(or) / Socia(o)	Empleador
Trabajadora(or) familiar o aprendiz sin remuneración	Aprendiz S/R
Trabajadora(or) del hogar	Trabajador/a del hogar
Cooperativista de producción / Servicios	Cooperativista

[2]El código empleado en el documento se encuentra en el CD que acompaña el documento

Se debe tener en cuenta que esta pregunta corresponde a las personas de 7 años o más, cuya condición de ocupación sea *Ocupado*.

5.2.4. Variable: Actividad económica

Corresponde a la pregunta 44 del cuestionario censal, esta pregunta es abierta pero existe una codificación en la base de datos a nivel de las ramas de actividad, estas son:

- Agropecuaria/silvicultura
- Mineria
- Manufactura
- Suministro de energia
- Suministro de agua
- Construcción
- Comercio/reparación de vehículos
- Transporte y almacenamiento
- Alojamiento/Comida
- Información/comunicaciones
- Financieras/seguros
- Inmobiliaria
- Profesionales/científicas/técnicas
- Servicios administrativos y de apoyo
- Administración pública
- Servicios de Educación
- Servicios de salud / asistencia social
- Actividades artísticas / entretenimiento
- Otras actividades de servicios
- Actividades de los hogares privados como empleadores
- Servicios de organizaciones y órganos extraterritoriales

El gráfico fue una de araña, este considero únicamente a las 5 actividades mas frecuentes para cada departamento o municipio. Se debe tener en cuenta que esta pregunta corresponde a las personas de 7 años o más, cuya condición de ocupación sea *Ocupado*.

5.2.5. Variable: Años de educación

Corresponde a la pregunta 37 y 38 del cuestionario, estas preguntas capturan el nivel y curso mas alto de instrucción aprobado. Se considero solamente a las personas de 15 años o mas para la construcción de las figuras, esto con el fin de aislar los años de escolaridad de las personas que aun están en la educación regular[3]. El gráfico empleado fue el de *gauge*, este es un medidor con limites y marca la posición actual de los años de educación de los inmigrantes o emigrantes, los limites elegidos fueron 0 años de educación y 12 años de educación que corresponde al ciclo de educación regular (primaria y secundaria).

5.2.6. Identificación indígena

Para la definición de este indicador se tomo en cuenta las preguntas 29, 30 y 31 del cuestionario censal, en base a estas preguntas se creo una variable dicótoma que permitió identificar (asignar) a las personas como pertenecientes o no de un pueblo originario, se considero perteneciente si cumplía con al menos una de las condiciones:

- Se considera perteneciente a algún pueblo indígena originario campesino o afro boliviano,
- Si su idioma materno pertenece a algún pueblo originario
- Si dentro de los idiomas que habla se encuentra algún idioma perteneciente a algún pueblo originario

El gráfico empleado fue el de *gauge*, este es un medidor con limites y marca el porcentaje (%) de personas pertenecientes a algún pueblo originario de los inmigrantes o emigrantes, los limites van de 0 a 100 %

5.2.7. Procedencia y destino

En base a las matrices de migración se realizaron mapas departamentales y municipales que muestran el porcentaje de procedencia de inmigrantes y destino de los emigrantes según cada departamento y municipio. Se eligieron 4 intervalos, estos corresponden a cortes basados en el análisis de los datos del autor.

- **Casi Nula:** 0 a 5 %
- **Baja:** 6 a 20 %
- **Media:** 21 a 50 %
- **Alta:** 51 a 100 %

5.2.8. Flujo migratorio

Empleando las matrices de migración se realizo un gráfico de flujos (riverplot) que muestra el flujo migratorio interno de los 5 principales lugares de procedencia y destino para cada departamento y municipio, adicionalmente se incluye el saldo migratorio en cada gráfico.

[3]Recomendación UNICEF

6. Resultados

Los resultados principales de este trabajo son:

1. 9 fichas departamentales
2. 339 fichas municipales
3. Código Stata para la generación de las matrices de migración y la caracterización de inmigrantes y emigrantes
4. Código R para la generación de las figuras
5. Código Latex para la generación de las fichas

7. Conclusiones

Las conclusiones de este trabajo se resumen en:

- Se cuenta con fichas departamentales y municipales sobre la migración interna en Bolivia, estas pueden informar y apoyar la toma de decisiones en los gobiernos sub nacionales respectos sus políticas.
- El censo de población 2012 sigue siendo la fuente principal de información para las unidades políticas mas pequeñas y es necesario explotar al máximo la información que esta contiene
- El trabajo se centra en la migración de toda la vida, sin embargo, con los códigos ya creados es mas fácil replicar el trabajo para obtener las fichas para la migración reciente

Referencias

Bott, R. (2014). *Migraciones Internas en el Perú* (n.º 1). doi: 10.1007/s13398-014-0173-7.2

Bustillos, C. H. L., Layme, D. L., Morató, R. P., y Gordonava, A. H. (s.f.). Las Migraciones Bolivianas.

Crescencio Ruiz Chiapetto. (2016). Migración interna y desarrollo económico. , *6*(3), 727-736.

González, D. (2011). Migracion Interna. Taller Regional sobre " Potencialidades y aplicaciones de los datos censales ".

Guzmán Castelo, E. (2002). Definiciones y conceptos sobre la migración. *Logros y retos del Frente Indígena Oaxaqueño Binacional: una organización para el futuro de los migrantes indígenas*(2002), 1–36.

Kumar, B. (2004). Internal Migration in Nepal. En *Publication of central department of population studies (cdps)* (pp. 121–168).

Morató, R. P. (2011). *Perfil Migratorio de Bolivia.*

Morató, R. P., y García, J. M. (2011). Migración interna: una aproximación a sus factores asociados.

Romo Viramontes, R., Téllez Vázquez, Y., y Ramírez López, J. (2013). Tendencias de la migración interna en México en el periodo reciente. *La situación demográfica de México*, 83 – 106.

Sander, N. (2014). Internal Migration in Germany, 1995-2010: New Insights into East-West Migration and Re-urbanisation. *Comparative Population Studies*, *39*(5), 217–246. doi: 10.12765/CPoS-2014-04en

United Nations. (1970). *Methods of Measuring Internal Migration.* Nueva York: United Nations.

United Nations Population Division. (2013). Cross-national comparisons of internal migration: An update on global patterns and trends. *Population Division Technical Paper No. 2013/1*, 30.

Vega, R. L. (2007). *Medición de la migración con especial referencia a la fuente de datos censal (la medición de la migración en los Censos de Población y Vivienda en México)* (Inf. Téc.).

Villalón Cárdenas, G., Farías Caro, O., Acuña Acosta, E., y de Chile, S. (1992). *Migraciones Interna Regional 1992-2002.*

White, M. J. (2016). *International Handbook of Migration and Population Distribution.* Springer. doi: 10.1007/978-94-017-7282-2

A. Fichas departamentales

Para ver las fichas departamentales seguir los vínculos siguientes:

- Chuquisaca
- La Paz
- Cochabamba
- Oruro
- Potosi
- Tarija
- Santa Cruz
- Beni
- Pando

B. Fichas municipales

Para ver las fichas municipales seguir los vínculos siguientes:

- **CHUQUISACA**
    - Sucre
    - Yotala
    - Poroma
    - Villa Azurduy
    - Tarvita (Villa Arias)
    - Zudanez
    - Presto
    - Villa Mojocoya
    - Icla (R.Mujia)
    - Padilla
    - Tomina
    - Sopachuy
    - Villa Alcala
    - El Villar
    - Monteagudo
    - San Pablo de Huacareta
    - Tarabuco
    - Yamparaez

- Camargo
- San Lucas
- Incahuasi
- Villa Charcas
- Villa Serrano
- Villa Abecia
- Culpina
- Las Carretas
- Villa Vaca Guzman (Muyupampa)
- Huacaya
- Machareti

- **LA PAZ**
  - Nuestra Senora de La Paz
  - Palca
  - Mecapaca
  - Achocalla
  - El Alto
  - Achacachi
  - Ancoraimes
  - Chua Cocani
  - Huarina
  - Santiago de Huata
  - Huatajata
  - Coro Coro
  - Caquiaviri
  - Calacoto
  - Comanche
  - Charana
  - Waldo Ballivian
  - Nazacara de Pacajes
  - Santiago de Callapa
  - Puerto Acosta
  - Mocomoco
  - Puerto Carabuco
  - Humanata
  - Escoma

- Chuma
- Ayata
- Aucapata
- Sorata
- Guanay
- Tacacoma
- Quiabaya
- Combaya
- Tipuani
- Mapiri
- Teoponte
- Apolo
- Pelechuco
- Viacha
- Guaqui
- Tiahuanacu
- Desaguadero
- San Andres de Machaca
- Jesus de Machaca
- Taraco
- Luribay
- Sapahaqui
- Yaco
- Malla
- Cairoma
- Inquisivi
- Quime
- Cajuata
- Colquiri
- Ichoca
- Licoma (Villa Libertad)
- Chulumani
- Irupana
- Yanacachi
- Palos Blancos
- La Asunta

- Pucarani
- Laja
- Batallas
- Puerto Perez
- Sica Sica
- Umala
- Ayo Ayo
- Calamarca
- Patacamaya
- Colquencha
- Collana
- Coroico
- Coripata
- Ixiamas
- San Buenaventura
- Charazani (Gral.Perez)
- Curva
- Copacabana
- San Pedro de Tiquina
- Tito Yupanki
- San Pedro de Curahuara
- Papel Pampa
- Chacarilla
- Santiago de Machaca
- Catacora
- Caranavi
- Alto Beni

- **COCHABAMBA**
  - Cochabamba
  - Aiquile
  - Pasorapa
  - Omereque
  - Independencia
  - Morochata
  - Cocapata
  - Tarata

- Anzaldo
- Arbieto
- Sacabamba
- Arani
- Vacas
- Arque
- Tacopaya
- Capinota
- Santibanez
- Sicaya
- Cliza
- Toko
- Tolata
- Quillacollo
- Sipe Sipe
- Tiquipaya
- Vinto
- Colcapirhua
- Sacaba
- Colomi
- Villa Tunari
- Tapacari
- Totora
- Pojo
- Pocona
- Chimore
- Puerto Villarroel
- Entre Rios (Bulo Bulo)
- Mizque
- Vila Vila
- Alalay
- Punata
- Villa Rivero
- San Benito
- Tacachi
- Cuchumuela (V. G.Villarroel)

- Bolivar
- Tiraque
- Shinahota

- **ORURO**
  - Oruro
  - Caracollo
  - El Choro
  - Paria
  - Challapata
  - Santuario de Quillacas
  - Corque
  - Choquecota
  - Curahuara de Carangas
  - Turco
  - Huachacalla
  - Escara
  - Cruz de Machacamarca
  - Yunguyo del Litoral
  - Esmeralda
  - Poopo
  - Pazna
  - Antequera (Bolivar)
  - Villa Huanuni
  - Machacamarca
  - Salinas de Garci Mendoza
  - Pampa Aullagas
  - Sabaya
  - Coipasa
  - Chipaya
  - Toledo
  - Eucaliptus
  - Santiago de Andamarca
  - Belen de Andamarca
  - San Pedro de Totora
  - Santiago de Huari
  - La Rivera

- Todos Santos
- Carangas
- Santiago de Huayllamarca

- **POTOSI**
  - Potosi
  - Tinguipaya
  - Yocalla
  - Belen de Urmiri
  - Uncia
  - Chayanta
  - Llallagua
  - Chuquihuta
  - Betanzos
  - Chaqui
  - Tacobamba
  - Colquechaca
  - Ravelo
  - Pocoata
  - Ocuri
  - San Pedro de Buena Vista
  - Toro Toro
  - Cotagaita
  - Vitichi
  - Sacaca
  - Caripuyo
  - Tupiza
  - Atocha
  - Colcha"K" (V.Martin)
  - San Pedro de Quemes
  - San Pablo de Lipez
  - Mojinete
  - San Antonio de Esmoraca
  - Puna
  - Caiza "D"
  - Ckochas
  - Uyuni (Thola Pampa)

- Tomave
- Porco
- Arampampa
- Acasio
- Llica
- Tahua
- Villazon
- San Agustin

- **TARIJA**
  - Tarija
  - Padcaya
  - Bermejo
  - Yacuiba
  - Carapari
  - Villamontes
  - Uriondo
  - Yunchara
  - Villa San Lorenzo
  - Tomayapo (El Puente)
  - Entre Rios (La Moreta)

- **SANTA CRUZ**
  - Santa Cruz de la Sierra
  - Cotoca
  - Porongo (Ayacucho)
  - La Guardia
  - El Torno
  - Warnes
  - Okinawa Uno
  - San Ignacio de Velasco
  - San Miguel de Velasco
  - San Rafael
  - Buena Vista
  - San Carlos
  - Yapacani
  - San Juan de Yapacani

- San Jose de Chiquitos
- Pailon
- Robore
- Portachuelo
- Santa Rosa del Sara
- Colpa Belgica
- Lagunillas
- Charagua
- Cabezas
- Cuevo
- Gutierrez
- Camiri
- Boyuibe
- Vallegrande
- Trigal
- Moro Moro
- Postrer Valle
- Pucara
- Samaipata
- Pampa Grande
- Mairana
- Quirusillas
- Montero
- General Saavedra
- Mineros
- Fernandez Alonso
- San Pedro
- Concepcion
- San Javier
- San Ramon
- San Julian
- San Antonio de Lomerio
- Cuatro Canadas
- San Matias
- Comarapa
- Saipina

- Puerto Suarez
- Puerto Quijarro
- Carmen Rivero Torrez
- Ascencion de Guarayos
- Urubicha
- El Puente

- **BENI**
  - Trinidad
  - San Javier
  - Riberalta
  - Guayaramerin
  - Reyes
  - San Borja
  - Santa Rosa
  - Rurrenabaque
  - Santa Ana de Yacuma
  - Exaltacion
  - San Ignacio
  - Loreto
  - San Andres
  - San Joaquin
  - San Ramon
  - Puerto Siles
  - Magdalena
  - Baures
  - Huacaraje

- **PANDO**
  - Cobija
  - Porvenir
  - Bolpebra (Mukden)
  - Bella Flor
  - Puerto Rico
  - San Pedro (Conquista)
  - Filadelfia
  - Puerto Gonzales Moreno

- San Lorenzo
- El Sena
- Santa Rosa del Abuna
- Ingavi
- Nuevo Manoa (Nueva Esperanza)
- Villa Nueva (Loma Alta)
- Santos Mercado